В. И. Іохельсонъ.

Международные Конгрессы Американистовъ.

Древнія и современныя подземныя жилища племенъ сѣверо-восточной Азіи и сѣверо-западной Америки.

Международные Конгрессы Американистовъ.

(Читано въ засѣданіи Русскаго Антропологическаго Общества при С.-Петерб. университетѣ 17 января 1908 г.).

Мое сообщеніе будетъ состоять изъ двухъ частей: изъ краткихъ свѣдѣній по исторіи международныхъ конгрессовъ Американистовъ и изъ моего доклада о подземныхъ жилищахъ на сѣверо-востокѣ Азіи и сѣверо-западѣ Америки,—доклада, прочитаннаго на XV международномъ конгрессѣ Американистовъ въ городѣ Квебекѣ, въ Канадѣ, въ августѣ 1906 года [1]).

Докладъ этотъ,—теперь мною нѣсколько измѣненный,—былъ прочитанъ на конгрессѣ въ моемъ отсутствіи и напечатанъ на англійскомъ языкѣ въ отчетахъ указаннаго конгресса. Дѣло въ томъ, что лѣтомъ 1906 года я, будучи въ Лондонѣ, расчитывалъ оттуда ѣхать въ Америку, и Антропологическое Общество при С.-Петербургскомъ университетѣ удостоило меня полномочіемъ представить его на конгрессѣ въ качествѣ оффиціальнаго делегата [2]). Но обстоятельства сложились такъ, что моя поѣздка въ Америку не состоялась. Поэтому я послалъ свой докладъ въ бюро конгресса съ просьбой представить его конгрессу въ моемъ отсутствіи. Такимъ образомъ, я выполнилъ возложенное на меня Антропологическимъ Обществомъ порученіе только отчасти, то есть, составленіемъ доклада, и представить теперь отчетъ о конгрессѣ, на которомъ лично не присутствовалъ, не могу; но, взамѣнъ отчета о Квебекскомъ конгрессѣ, я по-

---

[1]) См. *Woldemar Jochelson,* Past and present subterranean Dwellings of the Tribes of north-eastern Asia and north-western America. Congrès International des Américanistes, XV Session tenue à Québec en 1906, Tome II, Québec 1907, pp. 115—128.

[2]) См. Ibid. Tome I, p. XII.

зволю себѣ представить краткій обзоръ исторіи конгрессовъ Американистовъ вообще, конгрессовъ, очень мало извѣстныхъ въ Россіи.

Международные конгрессы Американистовъ, то есть, съѣзды лицъ различныхъ странъ, занимающихся изученіемъ Америки, возникли въ 1875 году по иниціативѣ Французскаго Общества Американистовъ (Société Américaine de France) въ Парижѣ. Это ученое общество назначило въ 1875 году мѣстомъ для перваго конгресса городъ Нанси во Франціи и содѣйствовало организаціи конгресса и выработкѣ статутовъ. Согласно этимъ статутамъ, задачи международныхъ конгрессовъ Американистовъ заключаются въ содѣйствіи этнографическому, лингвистическому и историческому изслѣдованіямъ сѣверной и южной Америки, главнымъ образомъ до-Колумбійскаго періода, и въ установленіи связи между лицами различныхъ странъ, занимающимися упомянутыми изслѣдованіями. Конгрессы должны были происходить черезъ каждые два года въ разныхъ странахъ попеременно. Организаціонный комитетъ составлялся изъ ученыхъ и меценатовъ города, назначеннаго для конгресса; только для перваго конгресса, въ городѣ Нанси, въ помощь мѣстному организаціонному комитету Парижское общество Американистовъ назначило делегацію изъ среды своихъ членовъ. Бюро конгресса, состоявшее изъ одного президента и четырехъ вице-президентовъ, выбиралось изъ лицъ, пребывающихъ въ томъ городѣ, гдѣ засѣдалъ конгрессъ. Совѣтъ конгресса составлялся изъ представителей всѣхъ странъ, пославшихъ делегатовъ. Этотъ совѣтъ назначалъ страну и городъ для засѣданій слѣдующаго очередного конгресса. Такимъ образомъ, на конгрессѣ въ Нанси, который былъ весьма многолюденъ (по числу членскихъ взносовъ числилось въ спискахъ около 2,000 человѣкъ), былъ выбранъ для засѣданій слѣдующаго конгресса, 1877 года, городъ Люксембургъ. Съ самаго начала въ международныхъ конгрессахъ Американистовъ принимали участіе наиболѣе выдающіеся ученые Европы, интересующіеся той или другой отраслью науки о человѣкѣ. Такъ, въ числѣ участниковъ мы встрѣчаемъ имена Дарвина, Леббока, Макса Мюллера, Штейнталя, Вир-

жова и многихъ другихъ. Но какъ это ни странно, конгрессы Американистовъ, международное ученое общество, имѣющее цѣлью изученіе Америки, не только возникли, но и происходили въ началѣ исключительно въ Европѣ. По словамъ проф. фонъ-денъ-Штейнена, ученые сѣверной и южной Америки явились впервые делегатами только на седьмомъ конгрессѣ, въ 1888 году, засѣдавшемъ въ Берлинѣ [1]). На десятомъ международномъ конгрессѣ Американистовъ, въ 1894 году, имѣвшемъ мѣсто въ Стокгольмѣ, получилось приглашеніе отъ мексиканцевъ устроить слѣдующій очередной конгрессъ 1896 года въ Мексикѣ. Предложеніе это вызвало оживленные дебаты. Были противники перенесенія конгрессовъ въ Новый Свѣтъ. Особеннымъ противникомъ этой идеи былъ Вирховъ. По его мнѣнію, перенесеніе конгрессовъ въ Америку значило бы предоставить ихъ различнымъ случайностямъ. Подъ этимъ подразумѣвалось опасеніе, что преемственность и органическое единство конгрессовъ ослабѣетъ и что на американскихъ конгрессахъ будетъ, благодаря отдаленности различныхъ частей Америки отъ Стараго Свѣта, мало европейскихъ делегатовъ, и обратно. Кромѣ того, въ нежеланіи перенесенія конгрессовъ для изученія Америки въ самую Америку можно было видѣть недовѣріе къ научнымъ силамъ американцевъ, хотя, надо замѣтить, что въ то время работы Этнологическаго Бюро въ Вашингтонѣ, основаннаго правительствомъ Сѣверо-Американскихъ Соединенныхъ Штатовъ въ 1879 году и подчиненнаго имъ Смитсоніанскому институту, уже достаточно доказали, что европейскіе этнологи многому могли бы научиться у своихъ сѣверо-американскихъ коллегъ по части собиранія матеріаловъ, обработки ихъ и способа публикаціи трудовъ. Между прочимъ, профессоръ Вирховъ, главный противникъ перенесенія конгрессовъ въ Новый

---

[1]) См. International Congress of Americanists, Thirteenth Session held in New-York in 1902, p. LV. Надо замѣтить, что въ спискахъ делегатовъ мы встрѣчаемъ имена американскихъ ученыхъ также въ отчетахъ конгрессовъ до 1888 Такъ напр., въ предварительныхъ спискахъ делегатовъ на конгрессѣ Американистовъ въ Люксембургѣ мы встрѣчаемъ имя проф. Генри, директора Смитсоніанскаго института въ Вашингтонѣ. Мнѣ неизвѣстно, присутствовалъ ли онъ на конгрессѣ. Отчета о конгрессѣ въ Люксембургѣ не оказалось въ библіотекѣ Академіи Наукъ.

Свѣтъ, много сдѣлавшій по антропологіи американскихъ расъ, былъ все-таки американистомъ, никогда не бывавшимъ въ Америкѣ. Чтобы примирить разногласіе, Стокгольмскій конгрессъ принялъ предложеніе мексиканцевъ, но назначилъ въ Мексикѣ на 1895 годъ экстраординарный конгрессъ, въ то время какъ очередной конгресъ 1896 года долженъ былъ имѣть мѣсто въ Голландіи.

Къ сожалѣнію, опасенія противниковъ перенесенія конгрессовъ въ Америку оправдались, несмотря на успѣхъ конгресса въ 1895 году въ странѣ ацтековъ. Очередной конгрессъ 1896 года въ Нидерландахъ не состоялся, и только въ 1900 году связь Американистовъ съ Европой возобновилась и, опять-таки, благодаря иниціативѣ и усиліямъ французовъ, среди которыхъ еще со времени пребыванія въ Парижѣ Александра фонъ-Гумбольдта, перваго ученаго изслѣдователя Америки, и его друзей, мы находимъ много ревностныхъ американистовъ.

Въ 1900 году Парижское Общество Американистовъ (Société Americaine de Paris), основанное въ 1895 году, организовало въ Парижѣ двѣнадцатый международный конгрессъ Американистовъ. На этомъ конгрессѣ былъ выработанъ новый уставъ, въ который внесены существенныя измѣненія, сравнительно съ уставомъ 1875 года. Конгрессы собираются разъ въ два года, но попеременно въ Старомъ и Новомъ Свѣтѣ, при этомъ два очередныхъ конгресса той или другой части свѣта не должны происходить подъ рядъ въ одной и той же странѣ. Такъ, напримѣръ, послѣ Парижскаго конгресса 1900 года, слѣдующій очередной конгрессъ Стараго Свѣта, конгрессъ 1904 года, не могъ уже происходить во Франціи. Другими важными измѣненіями въ статутахъ были слѣдующіе пункты. По статутамъ 1875 года, сообщенія на конгрессахъ могли быть сдѣланы на одномъ изъ пяти европейскихъ языковъ (французскомъ, нѣмецкомъ, англійскомъ, испанскомъ и итальянскомъ), но дѣловымъ языкомъ, какъ международный, считался французскій. Теперь дѣловымъ языкомъ служитъ языкъ той страны, гдѣ засѣдаетъ конгрессъ, а сообщенія на конгрессахъ можно, какъ и раньше, дѣлать на одномъ изъ указанныхъ языковъ. Вице-предсѣдателей выбирается шесть: два

изъ мѣстныхъ членовъ конгресса, четыре изъ иностранныхъ представителей. Такимъ образомъ, послѣ Парижскаго конгресса 1900 года въ Новомъ Свѣтѣ уже имѣли мѣсто два конгресса, одинъ въ Нью-Іоркѣ въ 1902 году и другой въ Квебекѣ, въ Канадѣ, въ 1906 году. Въ Старомъ же Свѣтѣ за это время состоялся одинъ конгрессъ въ 1904 году, въ Штуттгартѣ. Въ настоящемъ году, въ сентябрѣ, конгрессъ снова соберется въ Европѣ, именно, въ Вѣнѣ.

Общество международныхъ конгрессовъ Американистовъ показало, насколько полезны для науки международные ученые институты. Ко времени возникновенія конгрессовъ Американистовъ мы видимъ не мало изслѣдователей, строившихъ самыя неосновательныя теоріи о происхожденіи американской расы и древнихъ культуръ. Такъ, напримѣръ, происхожденіе найденныхъ по открытіи испанцами Америки высокихъ культуръ и искусства въ Мексикѣ, Перу и Юкатанѣ одни изъ европейскихъ ученыхъ приписывали древнему вліянію финикіянъ, другіе— египтянъ, буддистовъ, китайскихъ монаховъ, скандинавовъ, японцевъ и другихъ. Были и такіе изслѣдователи, которые приписывали религіозные обряды и архитектуру инковъ въ Перу потерявшимся десяти съ половиною колѣнамъ Израиля. Всѣ эти фантастическія гипотезы должны были стушеваться передъ изученіемъ памятниковъ, обмѣномъ мыслей спеціалистовъ и свѣтомъ критики. Съ другой стороны, явившаяся теорія американскихъ ученыхъ,—какъ реакція противъ указанныхъ гипотезъ, — о совершенной самостоятельности американскихъ расы и культуръ, тоже должна была сдѣлать уступки при критическомъ обмѣнѣ мнѣній Американистовъ. Вопреки мнѣнію объ изолированности индѣйцевъ до открытія европейцами Америки и совершенной самостоятельности развитія высокихъ культуръ центральной и южной Америки до Колумба, несомнѣнно установлено, что древніе предки обитателей Америки, до или послѣ ледниковаго періода, изъ Азіи или Европы, разъ или нѣсколько разъ, явились туда переселенцами изъ Стараго Свѣта. Выясненію этихъ вопросовъ посвящены усилія и труды Американистовъ, и всякій, кто интересуется изученіемъ исторіи и археологіи Америки и изслѣдованіемъ современныхъ американскихъ племенъ, найдетъ въ

объемистыхъ отчетахъ. появляющихся въ свѣтъ послѣ каждаго конгресса, весьма обильный матеріалъ.

Остается еще сказать нѣсколько словъ объ участіи русскихъ въ работахъ Американистовъ. На конгрессы Американистовъ правительства и ученыя общества всѣхъ культурныхъ странъ Стараго и Новаго Свѣта посылаютъ оффиціальныхъ делегатовъ. Мы встрѣчаемся на конгрессахъ Американистовъ не только съ представителями скандинавскихъ странъ, открывшихъ сѣверо-восточную часть Америки 1000 лѣтъ тому назадъ, или романскихъ народовъ, открывшихъ центральную Америку 400 лѣтъ тому назадъ, или народовъ, пріобрѣвшихъ въ Америкѣ колоніи впослѣдствіи, но и съ представителями націй. никакой исторической или государственной связи съ Новымъ Свѣтомъ не имѣющихъ и преслѣдующихъ только научные интересы. Русскія же ученыя общества и другія учрежденія стоятъ какъ будто въ сторонѣ отъ научныхъ вопросовъ Американизма, а между тѣмъ, еще въ семнадцатомъ столѣтіи русскіе піонеры доказали, что Америка отдѣлена отъ Азіи проливомъ, а наши самоотверженные мореплаватели въ теченіи восемнадцатаго столѣтія впервые открыли и описали всю сѣверо-западную часть Америки, долгое время бывшую русской колоніею. Кромѣ того, близость сѣверо-восточной Сибири къ Америкѣ, физическое смѣшеніе и культурный обмѣнъ, который и теперь происходитъ между азіатскими чукчами и американскими эскимосами, должны были служить достаточнымъ стимуломъ для сравнительнаго изученія обѣихъ странъ. Только тогда, когда сѣверо-американскіе этнологи, придя къ убѣжденію, что для выясненія исторіи сѣверо-американскихъ индѣйцевъ, необходимо также изучить нѣкоторыя сибирскія племена, съ этой цѣлью обратились къ содѣйствію русскихъ изслѣдователей, послѣдніе стали принимать нѣкоторое участіе въ конгрессахъ Американистовъ. Такъ, на конгрессѣ 1902 года въ Нью-Іоркѣ присутствовалъ въ качествѣ гостя В. Г. Богоразъ; на конгрессѣ 1904 года въ Штутгартѣ г. Богоразъ былъ делегатомъ Московскаго Общества Любителей Естествознанія, а Л. Я. Штернбергъ, старшій этнографъ музея Академіи Наукъ, явился въ качествѣ делегата этого музея. Я тоже присутствовалъ на этомъ

конгрессѣ, но въ качествѣ одного изъ представителей американскаго музея естественныхъ наукъ въ Нью-Іоркѣ, такъ какъ на мой запросъ Географическому Обществу я получилъ отвѣтъ, что оно не имѣетъ въ виду командировать спеціальнаго делегата. На этомъ конгрессѣ были нами сдѣланы слѣдующія сообщенія: г. Богоразомъ—«О религіозныхъ идеяхъ примитивнаго человѣка на основаніи вѣрованій чукчей»; г. Штернбергомъ—«Объ отношеніи морфологіи гиляцкаго языка къ американскимъ»; мною—«Объ американскихъ и азіатскихъ элементахъ въ миѳахъ коряковъ» [1]). На послѣднемъ конгрессѣ Американистовъ, въ 1906 году, въ городѣ Квебекѣ, русскіе представители снова отсутствуютъ; былъ доложенъ только мой докладъ о подземныхъ жилищахъ въ сѣверо-восточной Азіи и сѣверо-западной Америкѣ, докладъ, который дальше приводится.

В. И. Іохельсонъ.

---

[1]) См. Internationaler Amerikanisten-Kongress, Vierzehnte Tagung, Stuttgart, 1904, Erste Hälfte. *W. Bogoras*, Religious Ideas of primitive Man, from Chukchee Material, pp. 130—135; *L. Sternberg*, Bemerkungen über Beziehungen zwischen der Morphologie der giljakischen und amerikanischen Sprachen, pp. 137—140; *W. Jochelson*, Über asiatische und amerikanische Elemente in den Mythen der Korjaken, pp. 119—127. Послѣднее сообщеніе въ русскомъ переводѣ напечатано въ «Землевѣдѣніи» книжка III, Москва, 1904, стр. 33—41.

Древнія и современныя подземныя жилища племенъ сѣверо-восточной Азіи и сѣверо-западной Америки.

(Читано въ засѣданіи Русскаго Антропологическаго Общества при С.-Петербургскомъ университетѣ 17 января 1908 г.).

Подземное или полу-подземное жилище различныхъ племенъ древности и отчасти настоящаго времени представляетъ собою продуктъ значительно высшей культуры, чѣмъ тотъ бытъ примитивнаго періода существованія человѣчества, когда для защиты отъ дождя, солнца, вѣтровъ и отъ нападенія враговъ люди прибѣгали къ естественнымъ убѣжищамъ, какъ пещеры, навѣсы, образуемые утесами, ущелья и дупла деревьевъ.

Съ теченіемъ времени первобытныя племена стали искусственно расширять или улучшать естественныя убѣжища. Въ извѣстныхъ случаяхъ первобытный человѣкъ достигъ большого искусства въ приспособленіи для жилья природой созданныхъ пещеръ и скалистыхъ навѣсовъ. Въ этомъ отношеніи глубокій интересъ представляютъ развалины древнихъ жилищъ, извѣстныхъ подъ именемъ жилищъ въ скалахъ (cliff dwellings), которыя находятся на плоскогоріи Аризоны, Новой Мексики, Колорадо и Юты, и прежніе обитатели которыхъ принадлежали къ группѣ племенъ, извѣстныхъ подъ именемъ Пуэбло. Эти племена дѣлали къ скалистымъ навѣсамъ пристройки изъ стѣнъ, сложенныхъ изъ камней, или искусственно углубляли пещеры въ болѣе мягкихъ горныхъ породахъ и, такимъ образомъ, образовали цѣлыя селенія и города въ скалахъ. Но эта архитектура, которая была выше тѣхъ построекъ, о которыхъ мы будемъ говорить, не входитъ въ предметъ нашего сообщенія.

Обозначеніе типа жилищъ, именемъ «подземныхъ» не всегда правильно, ибо только нѣкоторыя изъ нихъ находятся совершенно подъ землею, какъ напримѣръ, древнія искусственныя подземныя жилища, остатки которыхъ были найдены въ Шотландіи и Ирландіи; большая же часть такъ называемыхъ подземныхъ жилищъ находится подъ землею только въ большей или меньшей степени (приблизительно на половину или меньше), въ то время, какъ ихъ надземная часть покрыта землею, вынутой изъ ямы, въ которой жилище устроено. Всѣ эти жилища можно было бы обозначить общимъ именемъ землянокъ, если бы къ этому типу не принадлежали аналогичныя юрты, покрытыя сверху снѣгомъ, вмѣсто земли, какія мы находимъ у эскимосовъ и у отдѣла коряцкаго племени, извѣстнаго подъ именемъ керековъ. Поэтому я предпочелъ бы удержать за трактуемыми мною жилищами обще-признанное названіе «подземныхъ».

Для устройства остова подземнаго жилья употреблялись и теперь еще употребляются камни, дерево или кости большихъ млекопитающихъ, какъ китъ или лось. Подземныя жилища имѣли и теперь имѣютъ назначеніе защищать ихъ обитателей отъ холода и вѣтровъ, такъ что они, главнымъ образомъ, употребляются въ качествѣ зимнихъ жилищъ и встрѣчаются по преимуществу въ сѣверныхъ широтахъ Стараго и Новаго Свѣта. Другое назначеніе, очевидно, имѣли не такъ часто встрѣчаемыя подземныя жилища въ южныхъ широтахъ; такъ, напримѣръ, подземныя жилища восточной Африки, описанныя Лушаномъ [1]), или землянки въ Суданѣ, описанныя Фробеніусомъ, подземныя жилища въ южномъ Тунисѣ [2]) и полуподземныя жилища индѣйцевъ Калифорніи [3]). Эти жилища могли также служить защитой отъ палящихъ лучей лѣтняго солнца.

Въ Европѣ подземныя жилища были извѣстны всѣмъ ея древнимъ обитателямъ. Скиѳы жили въ подземныхъ

---

[1]) См. *Schurz*, Urgeschichte der Kultur. 1900, p. 423.

[2]) См. *D. Mac Ritchie*, Underground Dwellings (The Scottish Review, Jan. 18, 1906).

[3]) См. *Dixon*, The northern Maidu (Bulletin American Museum of Natural History, Vol. XVII, 1905, p. 168).

жилищахъ [1]). Тацитъ и Плиній приписываютъ ихъ древнимъ германцамъ [2]). Они были извѣстны франкамъ. Остатки найдены были въ Швейцаріи, Мекленбургѣ [3]) и Южной Баваріи [4]). Здѣсь они имѣли круглую форму, съ котлообразнымъ расширеніемъ на днѣ, діаметромъ отъ 11 до 15 метровъ и глубиною отъ 2 до 4 метровъ. Кельты, пикты [5]), славяне [6]), финны [7]) и лапландцы [8]) жили зимою въ землянкахъ. Къ сожалѣнію, мы не имѣемъ подробнаго описанія типовъ жилищъ этихъ племенъ. При постройкѣ желѣзныхъ дорогъ и во время военныхъ походовъ, какъ напримѣръ, въ послѣднюю русско-японскую войну, мы и теперь употребляемъ четырехъугольныя землянки въ качествѣ жилищъ для рабочихъ или войска, но эти землянки отличаются отъ другихъ подземныхъ жилищъ тѣмъ, что снабжены окнами въ надземной части стѣнъ, печами или каминами, трубы которыхъ выходятъ наружу.

Подземныя жилища были еще недавно въ употребленіи у венгерскихъ цыганъ [9]). Для ихъ устройства они копали ямы, глубиною отъ 10 до 12 футовъ. Крыша состояла изъ балокъ, положенныхъ поперекъ ямы и покрытыхъ соломой и дерномъ.

Остатки другого рода подземныхъ жилищъ были найдены въ Ирландіи [10]), Шотландіи [11]) и на небольшихъ островахъ къ сѣверу отъ Шотландіи [12]). Эти жилища представляли собою въ большинствѣ случаевъ длинные корри-

---

[1]) *M. Hoernes*, Die Urgeschichte des Menschen, Wien, 1892, p. 255.

[2]) *F. Maurer*, Ueber das Alter der Gruben-und Hölenbewohner, Ausland, 1870, p. 635.

[3]) *Lippert*, Kulturgeschichte der Menschheit, 1887, p. 204.

[4]) *Hoernes*, p. 265.

[5]) *D. Mac Ritchie*, Homes of The Picts (The Reliquary and Illustrated, Archaeologist, April, 1901).

[6]) *Lippert*, p. 205.

[7]) «*Ausland*», 1871, p. 741.

[8]) *D. Mac Ritchie*, Underground Dwellings (The Scottish Review).

[9]) *Lippert*, p. 204.

[10]) Mrs *Mary Hobson*, An Account of some Souterains in Ulster Ireland. (Paper read before The British Association, at its Meeting held at Leicester, England, 1907).

[11]) *David Mac Ritchie*, Subterranean Dwelling (The Antiquary, Vol. XXVI, London, 1892); *idem*, Underground Dwelling (Scotish Notes and Queries, March, 1900) *idem*, An Aberdeenshire Mound-Dwelling (The Antiquary, May, 1899).

[12]) *Idem*, The Interior of a Fairy Knoll (The Scottish Review, November, 9, 1905).

доры, глубиною отъ 8 до 10 футовъ и шириною около 8 футовъ. Нѣкоторыя изъ этихъ подземныхъ галлерей имѣли мѣстами узкіе проходы, расширенія или развѣтвленія въ видѣ отдѣльныхъ комнатъ, какъ у эскимосовъ. Стѣны и крыша соединены были безъ цемента, при помощи необтесанныхъ камней. Это было сдѣлано слѣдующимъ образомъ. Каждый верхній рядъ камней, образующихъ стѣны, выдвигался нѣсколько впередъ сравнительно съ нижнимъ рядомъ, такъ что верхніе ряды камней противоположныхъ стѣнъ сходились на верху, образуя родъ арки, извѣстной подъ названіемъ «циклопической» [1]). Сама крыша сдѣлана изъ широкихъ каменныхъ плитъ или изъ бревенъ. Характерная черта древнихъ подземныхъ жилищъ въ Шотландіи и Ирландіи состоитъ въ томъ, что они большей частью находились совершенно подъ землею и не образовали на поверхности земли никакихъ холмовъ или насыпей, при помощи которыхъ легко открывается древнее мѣстопребываніе подземныхъ жилищъ другихъ типовъ. Кромѣ того, входъ въ подземныя жилища Шотландіи и Ирландіи былъ настолько замаскированъ, что жилища эти, очевидно, имѣли главной цѣлью защиту отъ враговъ. Что же касается употребленія камней для устройства подземныхъ жилищъ или землянокъ вообще, то этотъ матеріалъ употреблялся также въ древней Арменіи и теперь употребляется эскимосами, за отсутствіемъ лѣса.

Изъ подземныхъ жилищъ Азіи я прежде всего упомяну землянки древней Арменіи [2]), на которыя я сейчасъ указалъ. По словамъ Ксенофонта, ямы этихъ подземныхъ жилищъ были расширены у основанія, и входили въ эти жилища при помощи лѣстницы. Древне-грузинскія подземныя жилища найдены около Тифлиса. Согласно устному сообщенію И. С. Джабадари, жители нѣкоторыхъ армянскихъ и грузинскихъ селеній, дома которыхъ были разрушены во время недавнихъ безпорядковъ, поселились въ землян-

---

[1]) Idem, Description of an Earth-House at Pitcur (Proceedings of The Antiquaries of Scottland, vol. XXXIV, p. 204).

[2]) См. *Hoernes*, p. 265.

кахъ. Фригійцы [1]) обкладывали свои жилища, сложенныя изъ камней, землею или дерномъ. Историкъ Сибири Миллеръ [2]) и этнологъ Патканов [3]) даютъ намъ свѣдѣнія о землянкахъ Обскихъ остяковъ, которыя въ настоящее время почти исчезли. Онѣ, очевидно, были обще-финскаго типа и представляли собою четырехъугольныя ямы, выложенныя лѣсомъ. Крыша, сдѣланная изъ жердей, была покрыта торфомъ и землею. Эти жилища не имѣли оконъ, отверстіе въ крышѣ служило одновременно для свѣта и выхода дыма. Это отверстіе помѣщалось или въ серединѣ крыши, или съ боку, въ зависимости отъ положенія очага въ самой землянкѣ. Въ землянку входили черезъ боковую дверь, къ которой велъ рядъ ступенекъ или просто земляной спускъ. Небольшая площадка передъ дверью, огороженная съ обѣихъ сторонъ жердями, для защиты входа отъ вѣтра, образовала сѣни.

Судя по описанію, сдѣланному недавно въ его сообщеніи въ Географич. Обществѣ изслѣдователемъ Енисейскихъ остяковъ, В. И. Анучинымъ, осеннія землянки этихъ остяковъ въ общемъ можно отнести къ финно-остяцкому типу.

Какъ мы увидимъ дальше, всѣ такъ называемые палеазіатскіе народы жили раньше или живутъ еще теперь въ подземныхъ жилищахъ. Въ сѣверной Америкѣ мы находимъ подземныя жилища у эскимосовъ, алеутовъ и многихъ индѣйскихъ племенъ. Въ виду данныхъ о разнообразіи формъ этихъ жилищъ и объ ихъ распространеніи среди племенъ, весьма удаленныхъ другъ отъ друга, мы должны допустить, что идея устройства подземныхъ жилищъ вытекала, хотя и изъ одинаковыхъ побужденій, но могла зародиться совершенно независимо у различныхъ народовъ. Однако мое изслѣдованіе подземныхъ жилищъ приморскихъ коряковъ и сравнительное изученіе описаній другихъ путешественниковъ подземныхъ или полу-подземныхъ жилищъ другихъ племенъ, обитающихъ на берегахъ Ледовитаго моря и въ сѣверной части Тихаго океана, привели

---

[1]) См. *Lippert*, p. 205.
[2]) *Миллеръ*, Исторія Сибири, стр. 129.
[3]) *С. Патканов*. Типъ остяцкаго богатыря по остяцкимъ былинамъ и героическимъ сказаніямъ. Спб., 1891, стр. 31.

меня къ заключенію, что подземныя жилища упомянутыхъ племенъ представляютъ собою не только продуктъ сходной культуры, но что они, вѣроятно, распространялись при помощи заимствованія. Такъ подземныя жилища палеазіатскихъ племенъ съ одной стороны похожи на подземныя жилища эскимосовъ и алеутовъ, а съ другой—на землянки индѣйцевъ. Этотъ вопросъ разсматривается полнѣе въ моей работѣ о матеріальной культурѣ коряковъ, составляющей часть трудовъ экспедиціи Джесупа [1]). Я займусь здѣсь краткимъ разсмотрѣніемъ подземныхъ жилищъ указанныхъ племенъ, какъ въ ихъ общихъ, такъ и въ частныхъ чертахъ.

Не вдаваясь въ разныя уклоненія того или иного типа, мы можемъ указать на слѣдующія характерныя черты подземныхъ жилищъ береговъ сѣверной части Тихаго океана. 1) Яма для жилища, круглой или неправильной формы, глубиною отъ 3 до 6 футовъ, обыкновенно выкапывается на холмѣ, съ тѣмъ, чтобы дождевая вода могла стекать внизъ по склону холма. 2) Стѣны сдѣланы изъ бревенъ, поставленныхъ въ ямѣ вертикально. Онѣ образуютъ прямоугольникъ или неправильный восьмиугольникъ, или имѣютъ круглую форму; стѣны на половину или на треть выходятъ надъ ямой, но эти надземныя части стѣнъ обкладываются землею, вынутою изъ ямы, на подобіе вала, или обносятся землей въ видѣ холма. 3) Крыша поддерживается четырьмя или болѣе столбами, стоящими въ серединѣ жилища, а уклоны крыши спускаются къ стѣнамъ. 4) Квадратное отверстіе въ крышѣ служитъ дверью, окномъ и для выхода дыма. Для входа въ жилище поставлено бревно съ зарубками, служащее лѣстницей.

Главныя особенности подземныхъ жилищъ каждаго изъ племенъ, перечисленныхъ ниже въ отдѣльности, суть слѣдующія.

Айны.—У Л. Шренка мы находимъ описаніе современной

---

[1]) См. *W. Jochelson*, The Koryak, Part II, Material Culture and Social Organisation, pp. 447—468; 637—645 (Publications of the Jesup North Pacific Expedition, Vol. VI, Part II, Leiden, 1908).

землянки айновъ въ южной части Сахалина [1]). Въ эту землянку входятъ теперь не черезъ отверстіе въ крышѣ, а черезъ боковую дверь. Крыша землянки выдается надъ входомъ настолько, что образуетъ навѣсъ въ видѣ сѣней со ступеньками, ведущими къ двери; очагъ въ землянкѣ находится ближе къ двери, чѣмъ къ другимъ стѣнамъ, но въ землянкахъ малыхъ размѣровъ очагъ помѣщается въ серединѣ. Очень большія землянки имѣютъ часто два очага, по угламъ, по обѣ стороны двери, съ отдѣльнымъ отверстіемъ въ крышѣ для выхода дыма надъ каждымъ изъ очаговъ. Часто отъ очага идетъ узкій подземный тунель наружу, для тяги. Нѣмецкій изслѣдователь, докторъ Гриммъ описываетъ современную землянку курильцевъ, то есть айновъ, на островѣ Шикотанъ [2]). У нихъ, говоритъ онъ, очагъ помѣщается въ правомъ углу землянки, со стороны двери, а сѣнями для землянки служитъ лѣтній шалашъ.

Говоря о землянкахъ современныхъ айновъ, нельзя обойти молчаніемъ въ высшей степени интересный вопросъ о томъ, какому племени слѣдуетъ приписать тѣ подземныя жилища, многочисленные остатки которыхъ были найдены на островѣ Сахалинѣ, на Іезо и другихъ японскихъ островахъ. Нѣкоторые ученые, главнымъ образомъ, японскій профессоръ Тсубой, стараются доказать, что эти подземныя жилища были обитаемы не айнами, а другимъ, до-айноскимъ племенемъ (по мнѣнію Тсубоя—эскимосами). Другіе изслѣдователи, какъ японскій профессоръ Коганеи [3]) и бывшій профессоръ въ Токіо Бельцъ [4]) приводятъ весьма основательные аргументы въ пользу того, что древніе обитатели этихъ подземныхъ жилищъ были именно предки современныхъ айновъ. Среди другихъ новѣйшихъ изслѣдователей айновъ, Л. Я. Штернбергъ [5]) высказывается въ

---

[1]) *Л. Шренкъ*, Объ инородцахъ Амурскаго края, томъ II, Спб., 1899, стр. 11.

[2]) *H. Grimm*, Beitrag zur Kenntniss der Koropokguru auf Yezo und Bemerkungen über Shikotan-Aino (Mitteilungen der Deutschen Gesellschaft für Natur- und Völkerkunde Ostasiens in Tokio, Band V, 1889—1892, pp. 369—373).

[3]) *Koganei*, Die Urbewohner Japans (Mitteilungen der Deutschen Gesellschaft für Natur- und Völkerkunde Ostasiens in Tokio, Band. IX, Teil 3, 1903, pp. 297—330).

[4]) *E Baelz.*, Zur Vor- und Urgeschichte Japans (Zeitschrift für Ethnologie, Berlin, 1907, pp. 281—310).

[5]) *Л. Я. Штернбергъ*. Гиляки, Москва, 1905, стр. 5. (Оттискъ изъ журнала «Этнографическое Обозрѣніе» кн. 60, 61 и 63).

пользу перваго мнѣнія, а д-ръ Лауферъ [1]) придерживается взглядовъ Коганеи и Бельца. Къ сожалѣнію, размѣры статьи не позволяютъ распространяться подробнѣе объ этомъ предметѣ, который разобранъ мною въ указанной выше работѣ о корякахъ [2]). Я хочу здѣсь только указать на то, что остатки подземныхъ жилищъ на островѣ Іезо, описанные докторомъ Гриммомъ, какъ и предметы, найденные при ихъ раскопкахъ, имѣютъ такое сходство съ остатками изслѣдованныхъ мною на берегахъ Гижигинскаго залива въ Охотскомъ морѣ древнихъ коряцкихъ землянокъ, что можно было бы принять раскопки на островѣ Іезо и въ Гижигинскомъ заливѣ за остатки древнихъ жилищъ одного и того же племени. И по отношенію къ размѣрамъ древнія подземныя жилища на островѣ Іезо не отличаются отъ размѣровъ древнихъ коряцкихъ землянокъ. По своей формѣ, говоритъ Гриммъ, онѣ приближаются къ четыреугольнику, стороны котораго имѣютъ въ длину отъ 4 до 7 метровъ, и глубина которыхъ приблизительно въ три четверти метра. Звеномъ между остатками подземныхъ жилищъ древнихъ коряковъ береговъ Охотскаго моря и остатками подобныхъ же жилищъ на островѣ Іезо и Сахалинѣ нужно считать землянки, остатки которыхъ были найдены докторомъ Пфейферомъ [3]), Лауферомъ [4]) и другими въ низовьяхъ и устьѣ рѣки Амура, и которыя, повидимому, можно приписать древнимъ гилякамъ.

Гиляки. — Тѣ изъ современныхъ гиляковъ, которые еще не переняли надземной постройки маньчжурскаго типа, и теперь еще живутъ въ подземныхъ жилищахъ. Для устройства гиляцкой землянки выкапывается яма, глубиною отъ 3 — 4 футовъ въ формѣ квадрата, стороны котораго равняются 20 или 22 футамъ. Въ серединѣ крыши находится отверстіе для дыма и свѣта, а входятъ въ жилище черезъ узкій проходъ, который спускается наклонно къ низкой двери, находящейся въ одной изъ стѣнъ юрты. Уровень земляного пола внутри жилья

---

[1]) *Berthold Laufer*, Die angeblichen Urvölker von Yezo u. Sakhalin (Centralblatt für Anthropologie, Ethnologie und Urgeschichte, Jena, 1900, Band V, Heft 6).

[2]) *W. Jochelson*. The Koryak, II, pp. 641—645.

[3]) См. *Шренкъ*, Амурскіе инородцы, II, стр. 141.

[4]) *Laufer*, Die angeblichen Urvölker von Yezo u Sakhalin, p. 329.

ниже порога двери. Очагъ, сдѣланный изъ деревяннаго колодца, набитаго утоптанной землей, помѣщается въ серединѣ жилища подъ самымъ отверстіемъ въ крышѣ для дыма. Л. Я. Штернбергъ полагаетъ [1]), что въ древности дымовое отверстіе гиляцкой юрты служило также и входнымъ, какъ у древнихъ камчадаловъ или у современныхъ коряковъ. Даже теперь это отверстіе употребляется гиляками въ качествѣ двери въ нѣкоторыхъ торжественныхъ случаяхъ. Во время медвѣжьяго праздника гилякъ со шкурой и мясомъ убитаго медвѣдя спускается въ юрту черезъ дымовое отверстіе по спеціально вставленному бревну съ зарубками. Въ концѣ праздника всѣ ритуальныя принадлежности, равно какъ кости медвѣдя, выносятся изъ юрты черезъ дымовое же отверстіе.

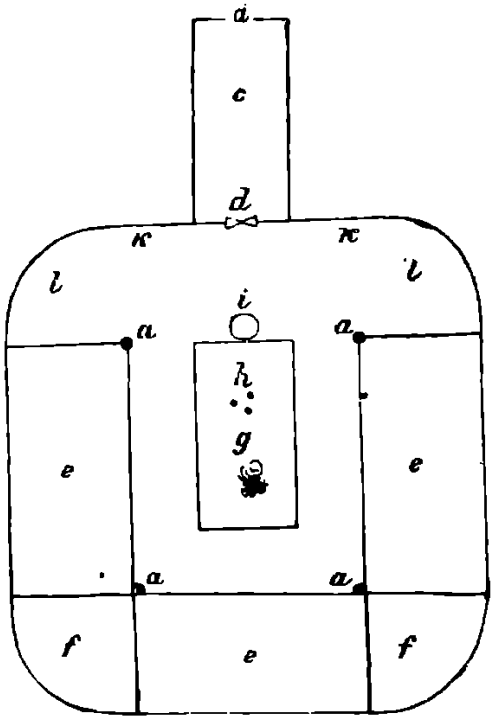

Фиг. 1.

Фиг. 1 изображаетъ планъ зимней подземной юрты гиляковъ (по Шренку); *a* — отвѣсные подпорные столбы; *c*—низкій проходъ; *d* — дверь; *e* — нары; *f*—задніе углы безъ наръ, служащіе кладовыми; *g*—очагъ; *h*—треуголь-

---

[1]) *Штернбергъ*, Гиляки, стр. 6.

никъ изъ камней для большого котла; *i*—водохранилище; *k*—передняя стѣна; *l*—передніе углы. Гиляцкій лѣтникъ устраивается на сваяхъ, какъ у древнихъ камчадаловъ, но менѣе высокихъ, чѣмъ у послѣднихъ.

Камчадалы. — Камчадалы въ настоящее время обрусѣли и болѣе не живутъ въ подземныхъ жилищахъ, мѣсто которыхъ заняли русскіе срубы или постройки якутскаго типа, тоже введенныя русскими. Но древнія зимнія жилища камчадаловъ, какъ они описаны Крашенинниковымъ [1]) и Штеллеромъ [2]), были подземныя юрты. Лѣтомъ камчадалы жили въ свайныхъ постройкахъ. Подземныя жилища камчадаловъ не имѣли сѣней или прохода, который мы встрѣчаемъ у коряковъ и гиляковъ. Дымовое отверстіе служило въ одно и то же время окномъ и дверью, черезъ которую спускались въ жилище по бревну съ зарубками. Это было единственное входное отверстіе, но вмѣсто сѣней или корридора, камчадальскія жилища имѣли подземный ходъ въ формѣ узкаго тунеля, который шелъ отъ очага и выходилъ наружу у одной изъ стѣнъ юрты. Тунель служилъ для тяги и былъ открытъ во время топки. По окончаніи топки выходное отверстіе тунеля закрывалось снаружи травяной затычкой. Тунель былъ настолько узокъ, что можно было черезъ него попасть въ юрту только ползкомъ. Мужчины считали за стыдъ входить въ юрту черезъ тунель, но дѣти и женщины ползали въ юрту черезъ этотъ ходъ. Этимъ ходомъ пользовались также такъ называемые коекчучи. Такъ камчадалы называли мужчинъ, одѣтыхъ въ женское платье и исполнявшихъ женскія работы. Камчадалы вѣрили, что и физическая природа этихъ переодѣтыхъ мужчинъ становится женской. Превращенные мужчины вступали въ качествѣ наложницъ въ сожительство съ мужчинами, но разумѣется, жили въ формѣ однополаго брака, воспѣваемаго нѣкоторыми изъ нашихъ новыхъ беллетристовъ и поэтовъ. Интересно замѣтить, что такія противоестественныя сожительства были извѣстны раньше корякамъ, эскимосамъ и нѣ-

---

[1]) *С. Крашенинниковъ*, Описаніе земли Камчатки, часть III, стр. 37—44, Спб. 1818.

[2]) *G. W. Steller*, Beschreibung von dem Lande Kamtschatka, Frankfurt und Leipzig, 1774, pp. 210—220.

которымъ индѣйскимъ племенамъ изъ группы атапасковъ, а въ настоящее время еще практикуются среди чукчей. Такія ненормальныя половыя отношенія развились подъ вліяніемъ идеи о шаманской силѣ, которую превращенные мужчины получаютъ отъ ихъ духовъ-покровителей по велѣнію и съ помощью которыхъ совершается будто бы перемѣна пола. Всѣ такіе субъекты считаются сильными шаманами. Эти вѣрованія находили себѣ почву въ индивидуумахъ съ ненормальнымъ физическимъ или психическимъ развитіемъ.

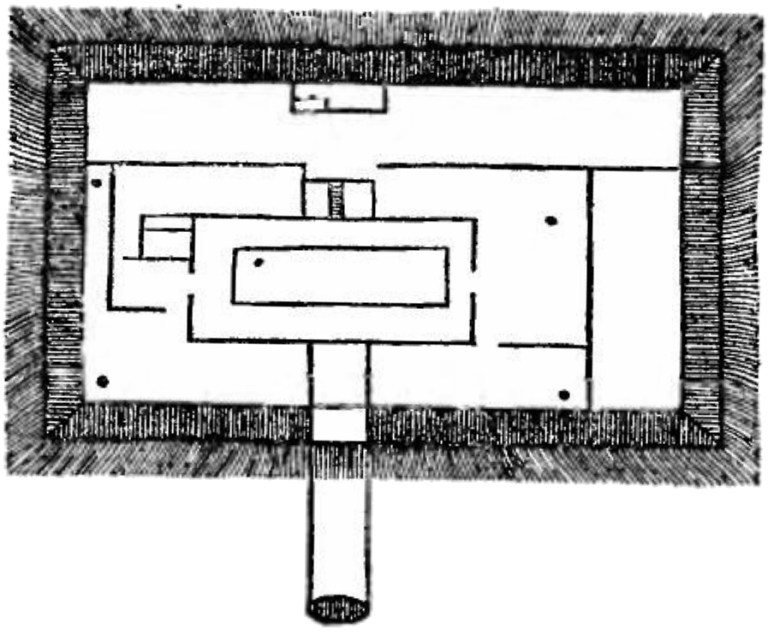

Фиг. 2.

Фиг. 2, заимствованная у Штеллера, показываетъ планъ зимняго жилья камчадаловъ. Въ нижней части рисунка

Фиг. 3.

изображенъ подземный тунель для тяги. Рисунокъ фиг. 3, взятый тоже у Штеллера, изображаетъ внутренность камчадальскаго подземнаго жилища. Въ серединѣ мы видимъ лѣстницу, очагъ и группу мужчинъ, а на нарахъ—женщинъ за работой.

Коряки.—Оленные коряки живутъ въ шатрахъ, обтянутыхъ оленьими шкурами, но сидячіе или приморскіе коряки, за исключеніемъ весьма небольшого количества обрусѣвшихъ коряковъ, и теперь обитаютъ въ подземныхъ жилищахъ. Коряцкое подземное жилище представляетъ нѣкоторыя особенности, по сравненію съ описанными мною выше. Яма имѣетъ глубину отъ 3 до 4 футовъ. Большая коряцкая юрта имѣетъ въ длину около 40 или даже больше футовъ. Она имѣетъ узкій корридоръ-сѣни, ведущія къ двери юрты, такимъ же образомъ, какъ у гиляковъ. Но этотъ проходъ открытъ только лѣтомъ. Тогда какъ камчадалы жили въ подземныхъ юртахъ только въ зимнее время, приморскіе коряки обитаютъ въ своихъ подземныхъ юртахъ также и лѣтомъ. На сваяхъ коряки строятъ только свои амбары для храненія провизіи. При наступленіи зимы дверь въ сѣни закрывается бревнами, обкладывается сухою травою, землею и снѣгомъ, и для входа въ жилище остается одно дымовое отверстіе, какъ у камчадаловъ. Чтобы спуститься въ юрту, коряки употребляютъ бревно, снабженное не зарубками, а дырьями, въ которыя вставляютъ концы ногъ. Подъ этой лѣстницей помѣщается очагъ, обложенный камнями, среди которыхъ разводится огонь. Крыша сѣней имѣетъ круглое отверстіе, которое закрывается затычкой, сдѣланной изъ плетеной травы на подобіе того, какъ камчадалы закрывали тунель для тяги въ своей юртѣ. Дѣйствительно, это приспособленіе имѣетъ то-же назначеніе, какое у камчадаловъ имѣлъ подземный ходъ, а именно для тяги. Когда на очагѣ разводится огонь, дверь изъ юрты, ведущей въ сѣни, открывается, и затычка въ крышѣ сѣней вынимается. Токъ воздуха тогда проникаетъ со двора черезъ отверстіе въ крышѣ сѣней въ юрту и гонитъ дымъ съ очага кверху въ выходное отверстіе. Интересная особенность коряцкой подземной юрты заключается въ той части ея крыши, которая имѣетъ форму опрокинутаго зонтика или воронки и защищаетъ входное

отверстіе отъ вѣтровъ, а самую юрту отъ снѣжныхъ заносовъ.

Такъ какъ коряковъ я самъ изучалъ, то позволю себѣ тутъ подробнѣе остановиться на описаніи внѣшняго и внутренняго устройства ихъ подземнаго жилища, иллюстрируя это описаніе рисунками и фотографіями, помѣщенными въ моей работѣ о корякахъ [1]).

Селенія приморскихъ или «сидячихъ» коряковъ расположены въ устьяхъ рѣкъ. По климатическимъ условіямъ, древесная растительность не доходитъ до морского берега. Какъ у Ледовитаго океана мы имѣемъ сѣверную или арктическую границу лѣсовъ, такъ у береговъ Охотскаго и Берингова морей мы тоже находимъ границу лѣсовъ, но юго-восточную. Берега этихъ морей на извѣстномъ разстояніи,—на 20 или больше верстъ,—совершенно лишены древесной растительности. Только въ болѣе или менѣе защищенныхъ отъ суровыхъ вѣтровъ долинахъ рѣкъ тополь или осина нерѣдко доходитъ до моря, но лиственница, наиболѣе прочное строительное дерево, отступаетъ отъ морскихъ береговъ по долинамъ рѣкъ далеко на сѣверо-западъ, въ сторону Станового хребта. Къ низовьямъ рѣкъ, — и то только сравнительно большихъ, какъ Пенжина или Гижига,—лиственница, вырванная бурнымъ весеннимъ ледоходомъ, проносится теченіемъ внизъ и выбрасывается на отмели и острова, образуя наносныя кучи, вышиной нерѣдко въ нѣсколько саженъ. Одна такая куча наноснаго

Фиг. 4.

[1]) См. *W. Jochelson*, The Koryak, Part I, p. 71, Part II, pp. 453—461

лѣса изображена на фиг. 4. Наносную лиственницу коряки употребляютъ главнымъ образомъ для постройки своего подземнаго жилья.

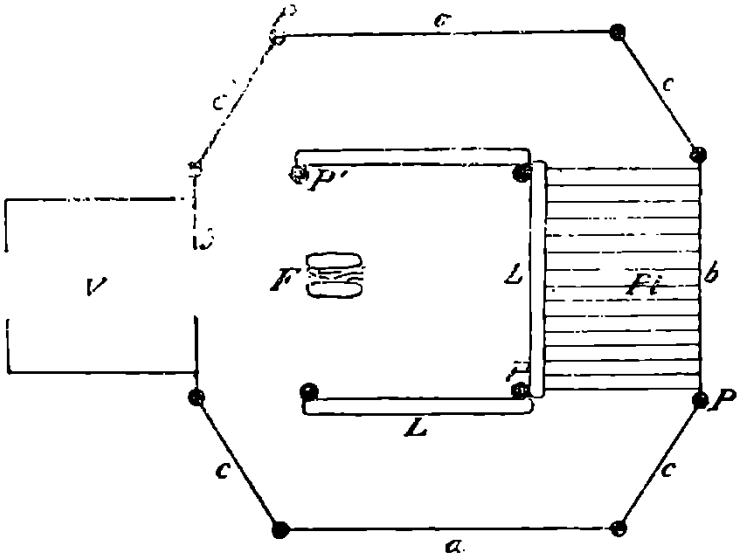

Фиг. 5.

Фиг. 5 изображаетъ планъ коряцкаго подземнаго жилья. *a*, *b* и *c* вертикальныя стѣны, сидящія въ землѣ; *P* — столбы между стѣнами; *P'* — центральные четыре столба, поддерживающіе верхнюю крышу и наклонныя ея части, идущія къ стѣнамъ; *F* — очагъ; *Pl* — высокія нары для гостей; *L* — бревна между столбами, отдѣляющія спальныя мѣста отъ центра юрты; *V* — сѣни, черезъ которыя входятъ въ юрту лѣтомъ.

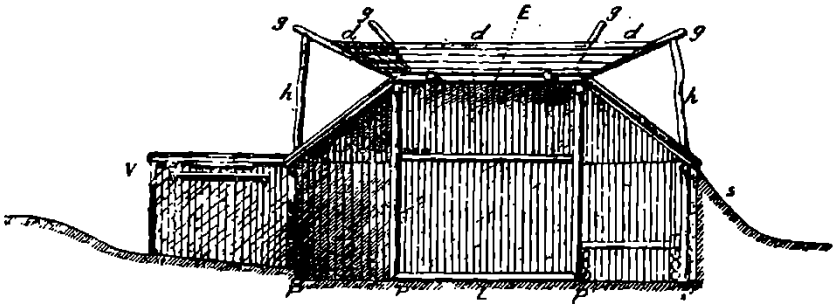

Фиг. 6.

Фиг. 6 показываетъ планъ коряцкой землянки, съ сѣнями и воронкой - щитомъ, въ вертикальномъ разрѣзѣ.

Фиг. 7 показываетъ устройство верхней части крыши

съ воронкообразнымъ щитомъ и входнымъ отверстіемъ (E). W—отверстіе въ крышѣ сѣней, служащее для тяги.

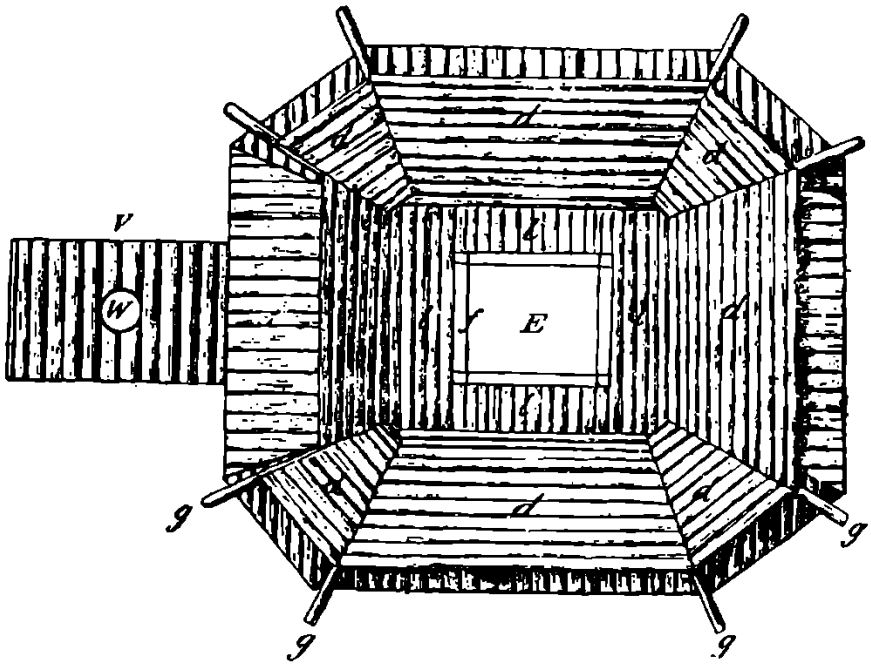

Фиг. 7.

Фиг. 8 есть снимокъ съ модели коряцкой землянки, вырѣзанной однимъ корякомъ изъ моржоваго зуба. Модель



Фиг. 8.

показываетъ всѣ части остова юрты, не обнесенной снаружи землей.

Фиг. 9 показываетъ коряцкую юрту зимой. Дверь въ сѣни заложена и занесена снѣгомъ. Изъ подъ снѣга выглядываетъ только воронка - щитъ. На крышѣ внутри

щита видны люди. На особыхъ шестахъ надъ крышей висятъ заколотыя въ жертву богамъ собаки.



Фиг. 9.

Фиг. 10 показываетъ, какъ дѣвушка съ ведромъ съ водой подымается по лѣстницѣ съ крыши сѣней на крышу

Фиг. 10.

юрты, съ тѣмъ, чтобы потомъ спуститься по такой же лѣстницѣ въ подземное жилье. На фиг. 11 мы видимъ крышу съ воронкой сверху. Это снято мной съ горы. На

крышѣ мы видимъ отверстіе для входа съ верхушкой лѣстницы. На крышѣ стоятъ двѣ нарты, и на одной изъ нихъ сидятъ двое дѣтей.

Фиг. 11.

Фигуры 12—16 показываютъ внутреннія стороны коряцкой землянки. Фиг. 12 изображаетъ шамана съ бубномъ, сидящаго на нарѣ, покрытой шкурами, на передней,

Фиг. 12.

почетной сторонѣ юрты. Переднюю сторону юрты мы видимъ также на фиг. 13. Здѣсь женщина шаманка, представительница семейнаго культа, шаманитъ по случаю удачнаго промысла тюленей. Члены семьи сидятъ на нарѣ и на полу у нары.

Фиг. 13.

Фиг. 14 представляетъ правую сторону юрты. На этой сторонѣ живетъ семья хозяина юрты или старшаго въ

Фиг. 14.

семьѣ, т. е. тутъ помѣщается его спальная палатка, но днемъ палатка снимается, и мѣсто это служитъ для сидѣнія и времепрепровожденія мужчинъ. На этой фотографіи изображено добываніе священнаго огня при помощи сверла и доски, имѣющей форму человѣка и считающейся покровителемъ семейнаго очага. Этотъ огонь добывается тутъ по случаю закрытія на зиму входа черезъ сѣни. Тогда тушатъ на очагѣ старый огонь и добываютъ новый, при помощи тренія священнымъ сверломъ.

Фиг. 15.

Фиг. 15 показываетъ лѣвую сторону коряцкой подземной юрты. На этой сторонѣ живутъ, т. е. имѣютъ свои спальныя палатки, младшіе члены семьи или семьи постороннихъ сожителей, но днемъ на этой сторонѣ проводятъ время женщины и дѣти. Женщины, не занятыя приготовленіемъ пищи у очага, здѣсь шьютъ одежду, обувь и исполняютъ другія женскія работы при тускломъ свѣтѣ каменной лампы. Лампа, т. е. каменная чашка, стоитъ на деревянной подставкѣ. Свѣтильнымъ матеріаломъ служитъ тюленій жиръ, а фитилемъ мохъ.

Фиг. 16 показываетъ заднюю сторону подземной коряцкой юрты, т. е. сторону съ дверью въ сѣни, очагъ и лѣстницу для подъема и спуска. Здѣсь видно, какъ лѣстница выходитъ въ отверстіе въ крышѣ. Лѣстница

стоитъ совершенно вертикально, и поднимаются по ней или спускаются, держась руками за стороны лѣстницы.



Фиг. 16.

Фиг. 17 изображаетъ часть селенія Большая Иткана, расположеннаго на Итканскомъ мысу въ Пенжинскомъ заливѣ Охотскаго края. Здѣсь мы видимъ цѣлый рядъ выглядывающихъ изъ подъ снѣга и окруженныхъ воронкообразными щитами крышъ землянокъ и разбросанныхъ между ними амбаровъ на высокихъ сваяхъ. Въ этомъ селеніи около 30 подземныхъ жилищъ и вдвое больше амбарчиковъ на столбахъ. Издали селеніе производитъ своеобразное впечатлѣніе своимъ сказочнымъ видомъ.

Фиг. 18 показываетъ скалистый обрывъ подъ устьемъ р. Пенжины, за которымъ скрывается Каменское селеніе.

Фиг. 19 представляетъ снимокъ съ амбара на сваяхъ.

Фиг. 20 изображаетъ шатеръ оленныхъ коряковъ. Шатеръ состоитъ изъ двухъ частей; нижней—цилиндрической и верхней—конической. Деревянный остовъ покрытъ оленьими шкурами. Переходъ отъ подземнаго жилья къ

шатру надо отнести къ тому времени, когда часть корякскаго племени сдѣлалась оленеводами.



Фиг. 17

Чукчи. — Чукчи, какъ сидячіе, такъ и оленные, дѣлаютъ въ настоящее время свои жилища изъ оленьихъ шкуръ, покрывающихъ деревянный остовъ, но вдоль береговъ Ледовитаго океана, начиная отъ Баранова Камня

Фиг. 18.



Фиг. 19.

Фиг. 20.

до Берингова пролива и вдоль береговъ Берингова моря, къ югу отъ пролива, можно и теперь еще найти остатки подземныхъ жилищъ чукчей, но остовъ этихъ жилищъ, за неимѣніемъ тамъ дерева, устраивался изъ китовыхъ костей.

Путешественникъ Врангель высказалъ мнѣніе [1]), что эти подземныя жилища были когда-то обитаемы эскимосами, впослѣдствіи переселившимися въ Америку. Другой писатель, англійскій географъ Маркгамъ [2]), на основаніи сходства между остатками подземныхъ жилищъ, найденныхъ на азіатскихъ берегахъ Ледовитаго океана, съ остатками жилищъ, найденныхъ на сѣверныхъ берегахъ и островахъ Америки, составилъ теорію о пути, по которому эскимосы двигались изъ Азіи въ Гренландію. На неосновательность этой теоріи и на болѣе вѣроятный путь, по которому эскимосы съ береговъ Гудзонова залива, а не изъ Азіи, эмигрировали въ Гренландію, указалъ въ одной изъ своихъ работъ объ эскимосахъ американскій профессоръ Боасъ [3]). Съ другой стороны академикъ Шренкъ высказалъ мнѣніе, что остатки подземныхъ жилищъ, найденныхъ на азіатскихъ берегахъ Ледовитаго океана и Берингова моря, были нѣкогда жилищами предковъ современныхъ чукчей, въ которыхъ они обитали, прежде чѣмъ заимствовали шатеръ, сдѣланный изъ оленьихъ шкуръ [4]). Это мнѣніе вполнѣ согласуется съ дѣйствительными фактами. Мнѣніе, приписывающее брошенныя подземныя жилища чукотской территоріи не предкамъ чукчей, а другому племени, было основано на разсказахъ самихъ чукчей о томъ, что эти подземныя жилища были нѣкогда обитаемы такъ называемыми онкилонами. Но онкилонъ есть не что иное, какъ неправильно записанное коряцко-

---

[1]) См. *Врангель*, Путешествіе, часть II, стр. 295, 333.

[2]) *R. Markham*, On the Origin and Migrations of the Greenland Esquimaux (The Journal of the Royal Geographical Society, London, Vol. XXXV, 1865, p. 87).

[3]) Dr. *F. Boas*, Ueber die ehemalige Verbreitung der Eskimo im Arktisch-amerikanischen Archipel (Zeitschrift der Gesellschaft für Erdkunde zu Berlin, Band. XVIII, 1883, p. 118). См. также *Boas*, The Eskimo of Baffin Land and Hudson Bay (Bulletin Amer. Mus. Nat. History, Vol. IX, 1901) p. 369 и *W. Thalbitzer*, Aphonetical Study of the Eskimo Language, Copenhagen, 1904 pp. 37—48.

[4]) *Шренкъ*, II, стр. 28.

чукотское слово *ангхаланъ*, что означаетъ приморскій житель. И теперь коряки, какъ и чукчи, примѣняютъ это слово ко всякому приморскому жителю, будь это чукча, эскимосъ, корякъ или камчадалъ. Въ поселкахъ на берегу Берингова моря чукчи разсказывали г. Богоразу, что въ подземныхъ жилищахъ, остатки которыхъ теперь найдены, жили когда-то ихъ предки [1]). Мы не имѣемъ подробнаго описанія чукотскихъ землянокъ, найденныхъ на берегахъ Ледовитаго океана [2]), но въ юго-восточной части Чукотскаго полуострова, на берегахъ Берингова моря, Богоразъ видѣлъ остатки такихъ жилищъ, какъ въ селеніяхъ приморскихъ чукчей, такъ и въ селеніяхъ азіатскихъ эскимосовъ, и подробно ихъ описалъ въ своей работѣ о чукчахъ [3]). Эти подземныя жилища, называемыя чукчами *валкаръ* (что означаетъ домъ изъ костей китовыхъ челюстей), также имѣли два входа, но въ противоположность устройству коряцкой землянки, верхнее отверстіе чукотскаго подземнаго жилища, которое находилось въ верхней части одной изъ стѣнъ, употреблялось именно лѣтомъ, въ то время, какъ зимою чукчи пользовались для входа узкимъ и длиннымъ подземнымъ тунелемъ, который лѣтомъ наполнялся водою. Полъ въ жиломъ помѣщеніи, расположенный выше уровня подземнаго хода, оставался свободнымъ отъ воды. Этотъ валкаръ имѣлъ остовъ изъ китовыхъ костей, замѣнявшихъ столбы, стропила и балки. Столбы поддерживались камнями, и весь остовъ, состоявшій изъ костей и реберъ кита, былъ покрытъ травою и дерномъ. Теперешніе обитатели нѣкоторыхъ селеній на Чукотскомъ полуостровѣ утверждаютъ, что имъ извѣстно, предки какихъ семействъ обитали въ тѣхъ или другихъ подземныхъ жилищахъ, руины которыхъ найдены въ ихъ сосѣдствѣ. Согласно ихъ утвержденіямъ, эти подземныя жилища оставлены были ихъ предками въ третьемъ поколѣніи. Интересно отмѣтить, что оленные коряки и теперь называютъ подземныя жилища своихъ приморскихъ родови-

---

[1]) *W. Bogoras*, The Chukchee, Part I, p. 181 (Publications of the Jesup North Pacific Expedition, Vol. VII, Leiden, 1904).

[2]) *Nordenskiöld*, Die Umsegelung Asiens und Europas auf der Vega, Bd. I, Leipzig, 1882, pp. 403—406.

[3]) См. *Bogoras*, The Chukchee. I, pp. 181—183.

чей именемъ валхай—слово, означающее, какъ и чукотское валкаръ—жилище, сдѣланное изъ костей китовыхъ челюстей. Въ настоящее время коряки употребляютъ для столбовъ, обшивки стѣнъ и для другихъ частей остова юрты исключительно дерево. Очевидно, что въ прежнее время коряки, подобно чукчамъ, алеутамъ и эскимосамъ, употребляли для своихъ построекъ также кости китовъ; но я долженъ прибавить, что среди частей остововъ раскопанныхъ мною древнихъ подземныхъ жилищъ коряковъ, я нигдѣ не нашелъ китовыхъ реберъ или челюстей, наоборотъ, кучи китовыхъ челюстей, реберъ и позвонковъ валялись на поверхности земли вокругъ деревянныхъ идоловъ—покровителей селеній—въ качествѣ жертвъ этимъ идоламъ.

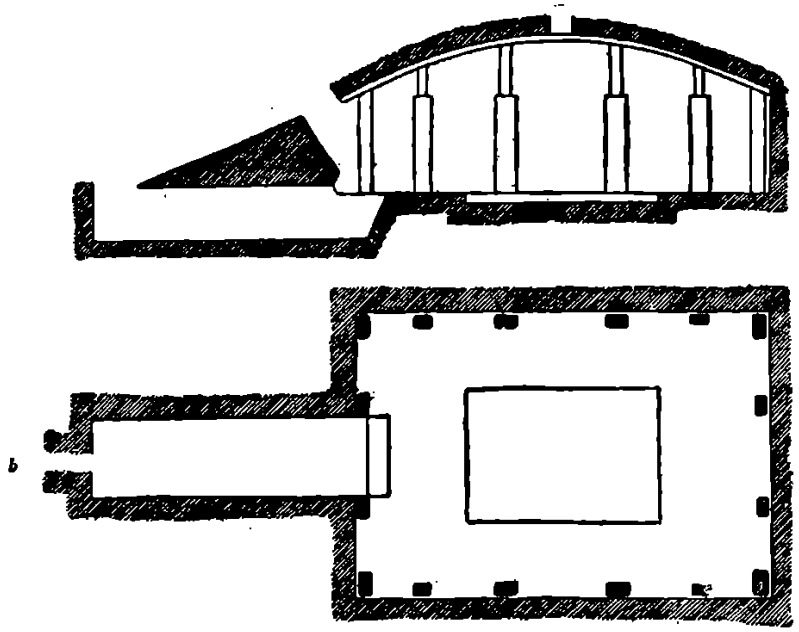

Фиг. 21.

Фиг. 21, заимствованная изъ работы Богораза о чукчахъ, показываетъ вертикальный (*a*) и горизонтальный (*b*) планъ чукотской подземной юрты изъ селенія Нунглингренъ на Чукотскомъ полуостровѣ. Столбы, поддерживающіе крышу, сдѣланы изъ распиленныхъ костей китовой челюсти съ надставками изъ китовыхъ реберъ. Перекладинами тоже служатъ китовыя ребра. По срединѣ жилья (см. *b*) лежитъ плоскій камень, на которомъ ставили жировую лампу. *C* есть зимній подземный тунель для входа

въ жилище. Лѣтомъ этотъ тунель наполнялся водой, а входили черезъ спускъ *D*. Зимой же входъ *D* затыкался травой и закрывался китовой лопаткой. Въ крышѣ имѣется отверстіе для свѣта. Въ настоящее время въ этомъ подземномъ жилищѣ, единственно сохранившемся еще у сидячихъ чукчей Чукотскаго полуострова, болѣе не живутъ, но оно еще служитъ мѣстомъ для сборищъ и церемоній, какъ эскимосскій кашимъ.

Юкагиры.— Въ настоящее время юкагиры живутъ въ кожаныхъ шатрахъ тунгускаго типа или въ домахъ-срубахъ, заимствованныхъ отъ русскихъ, но казаки, которые впервые столкнулись съ юкагирами, упоминаютъ въ своихъ отчетахъ о томъ, что послѣдніе живутъ въ землянкахъ. Казакъ Буза, боярскій сынъ Амосовъ, сержантъ Андреевъ и путешественники Геденштромъ и Врангель упоминаютъ объ остаткахъ подземныхъ жилищъ, видѣнныхъ ими въ устьяхъ рѣкъ Яны и Индигирки, на Медвѣжьихъ островахъ и на островахъ Новой Сибири [1]). Въ этихъ подземныхъ домахъ нѣкогда жили юкагиры. Это не оставляетъ никакого сомнѣнія въ томъ, что древній типъ жилища юкагировъ, во всякомъ случаѣ тѣхъ изъ нихъ, которые жили на морскомъ или рѣчныхъ берегахъ, была подземная юрта. Приходится сожалѣть, что въ указанныхъ отчетахъ и путешествіяхъ отсутствуетъ подробное описаніе остатковъ и устройства древнихъ юкагирскихъ землянокъ. Такимъ образомъ, мы не знаемъ въ точности, каковъ былъ типъ юкагирскаго подземнаго жилища. На рѣкѣ Ясачной и Коркодонѣ я видѣлъ современныя землянки юкагировъ, но эти землянки русскаго типа. Бревенчатый срубъ, на половину или больше сидящій въ ямѣ, обнесенъ землянымъ валомъ или завалинкой. Дверь и ледяныя окна находятся въ верхней части стѣны. Отапливается эта землянка якутскимъ камелькомъ съ трубою, выходящей наружу. Въ этихъ землянкахъ юкагиры живутъ только зимою; весною же и лѣтомъ они живутъ въ кожаныхъ шатрахъ конической формы.

---

[1]) *Врангель*, Путеш. Часть I, стр. 6;—часть II, стр. 141; *Геденштромъ*, Путеш. по Ледовитому морю («Сибирскій Вѣстникъ», 1822, стр. 105); Его же, Отрывки о Сибири. Спб. 1830, стр. 97); *Müller*, Samml. Russ. Gesch. III, p. 105; *Pallas*, Neue Nord. Beitr. I, 1787, pp. 234, 235.

Фиг. 22 показываетъ типъ современной юкагирской землянки на р. Коркодонѣ. Сѣни изъ жердей защищаютъ входъ въ полуподземный срубъ отъ заносовъ и вѣтровъ.

Фиг. 22.

Алеуты.—Описанія русскихъ и другихъ путешественниковъ, какъ Сарычевъ, Сауэръ, Веньяминовъ, Лангсдорфъ и Долъ (Dall) и др., изображаютъ древнія жилища алеутовъ весьма похожими на землянки камчадаловъ. Остовъ алеутскаго жилья былъ сдѣланъ изъ наноснаго лѣса или, если отсутствовалъ лѣсъ, изъ китовыхъ костей. Отверстіе въ крышѣ служило въ одно и то же время дверью, окномъ и для выхода дыма. Жилище отапливалось очагомъ, помѣщавшимся подъ дымовымъ отверстіемъ, а спускались въ жилище при помощи бревна съ зарубками. Кромѣ главнаго, жилого помѣщенія, у алеутовъ были другія, меньшихъ размѣровъ комнаты, соединенныя съ главнымъ помѣщеніемъ подземными проходами и снабженныя узкими тунелями, отверстія которыхъ выходили наружу и весьма напоминали тунель для тяги у камчадаловъ.

Эскимосы.—Начиная отъ береговъ Берингова моря и острова Кадьяка къ сѣверу, а затѣмъ къ востоку до самой Гренландіи и Лабрадора, мы вездѣ встрѣчаемъ остатки древнихъ подземныхъ жилищъ, но типъ этихъ жилищъ показываетъ нѣсколько разновидностей. Судя по описанію прежнихъ путешественниковъ, землянки алеутскаго типа встрѣчались въ южной части Аляски, съ тѣмъ, однако, отличіемъ, что рядомъ съ жилыми небольшихъ размѣровъ землянками, можно было встрѣтить общественныя подземныя помѣщенія или клубы, называемые эскимосами *кашимъ,* и назначенные для религіозныхъ церемоній, общественныхъ праздниковъ, игръ и паровыхъ бань. Въ нѣкоторыхъ мѣстахъ были найдены остатки землянокъ гиляцкаго типа. У Берингова пролива найдены были у эскимосовъ подзем-

ныя жилища вышеописаннаго чукотскаго типа валкаръ [1]). На американскихъ берегахъ Ледовитаго океана мы встрѣчаемъ остатки землянокъ, какъ этого типа, такъ и камчадальскаго со входомъ черезъ дымовое отверстіе. Остовъ этихъ эскимосскихъ землянокъ сдѣланъ изъ китовыхъ костей. Дальше къ востоку мы находимъ въ качествѣ матеріала для стѣнъ землянокъ камень [2]), какъ это мы видѣли при указаніи на устройство древне-шотландскихъ и грузинскихъ подземныхъ жилищъ, но съ той разницей, что крыша эскимосской землянки сдѣлана изъ китовыхъ костей. Каменныя стѣны часто сидятъ въ землѣ очень не глубоко или даже сложены на поверхности почвы, будучи обнесены землянымъ валомъ. На берегахъ Ледовитаго океана древнія эскимосскія подземныя жилища вытѣснены въ настоящее время почти вездѣ юртами, сдѣланными изъ снѣга. У эскимосовъ острова Кадьякъ, на рѣкѣ Юконѣ и на Аляскѣ вообще, почти до мыса Барро эскимосы отапливаютъ свои землянки наноснымъ лѣсомъ, но на островахъ св. Лаврентія, Діомеда и по берегу Ледовитаго океана до Гренландіи эскимосы нагрѣваютъ юрту жировой лампой. Въ эскимосскихъ подземныхъ жилищахъ, въ которыхъ живутъ только зимой, имѣется только одинъ входъ черезъ длинный тунель.

Приведу здѣсь иллюстраціи нѣсколькихъ типовъ эскимосскихъ землянокъ.

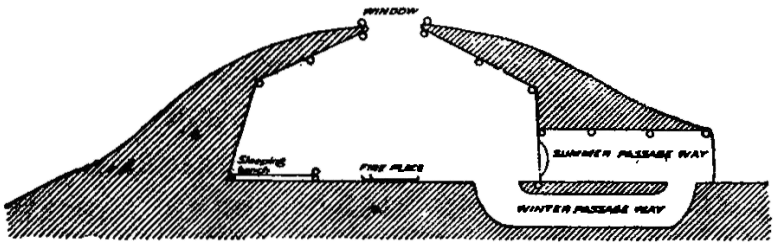

Фиг. 23.

---

[1]) См. *Murdoch*, Ethnological Results of the Point Barrow Expedition (Ninth Annual Report of the Bureau of Ethnology) Washington, 1892. p. 72; *Nelson*, The Eskimo about Bering Strait (Eighteenth Annual Report of the Bureau of Ethnology). Washington, 1889, p. 228.

[2]) См. *Boas*, The Central Eskimo (Sixth annual Report of the Bureau of Ethnology). Washington, 1888, p. 539; *Turner*, Ethnology of the Ungava District, Hudson Bay Territory (Eleventh Annual Report of the Bureau of Ethn.). Washington, 1889, p. 228.

Фиг. 23 (по Нельсону) изображаетъ планъ современной эскимосской землянки въ южной Аляскѣ. Она совершенно похожа на чукотскую землянку (см. фиг. 21). Эта землянка тоже имѣетъ два подземныхъ хода—нижній для зимы, верхній — для лѣта. Остовъ этой землянки сдѣланъ изъ дерева, а отверстіе въ крышѣ служитъ окномъ и для выхода дыма, такъ какъ очагъ отапливается наноснымъ лѣсомъ.

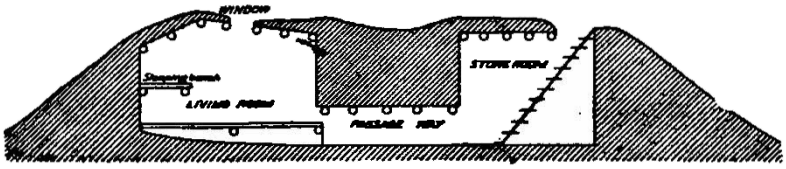

Фиг. 24.

Нѣсколько иной типъ представляетъ фиг. 24 (тоже по Нельсону). Это эскимосская землянка съ мыса Номъ. Подземный тунель, крыша котораго поддерживается столбами съ перекладинами, служитъ единственнымъ входомъ въ жилище. Спускаются въ тунель по лѣстницѣ, т. е. зарубленному бревну, черезъ пристройку - землянку, служащую амбаромъ и сѣнями. Въ такихъ сѣняхъ имѣется часто нѣсколько подземныхъ ходовъ, ведущихъ въ нѣсколько жилыхъ помѣщеній и въ отдѣльную кухню. Фиг. 25 показываетъ планъ такого жилища. Изъ передней-

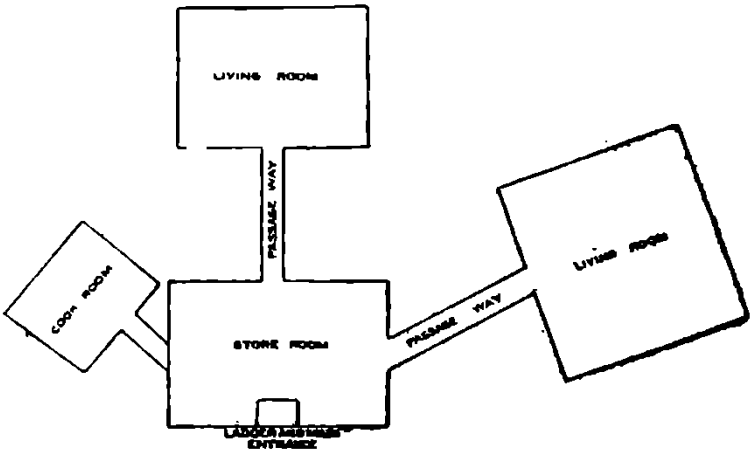

Фиг. 25.

кладовой два тунеля ведутъ въ жилыя помѣщенія, въ которыхъ живутъ различныя семьи, и одинъ тунель ведетъ

въ общую землянку - кухню. Подземные ходы имѣютъ въ длину 20 и больше футовъ, а въ высоту 3 фута, такъ что приходится идти ползкомъ.

Фиг. 26 (по Murdoch'у) показываетъ горизонтальный (*a*) и вертикальный (*b*) планъ эскимосской землянки съ мыса

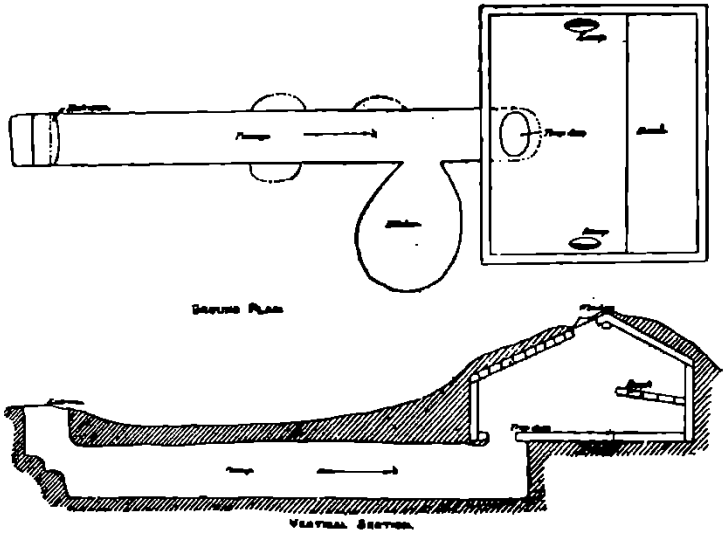

Фиг. 26.

Барро. Остовъ устраивается изъ наноснаго лѣса или китовыхъ костей. Землянка эта употребляется только, какъ зимнее жилье. Входъ одинъ—черезъ тунель, длиной около 25 футовъ и высотой около 4 футовъ. Спускаются въ тунель по ступенькамъ. Тунель поддерживается деревянными и костяными подпорками. Верхнее отверстіе тунеля закрывается деревянной крышкой или шкурой, а входъ изъ тунеля въ жилое помѣщеніе закрывается падающей дверью. Такимъ образомъ, жилое помѣщеніе защищено отъ наружнаго холода. Полъ, потолокъ и стѣны обшиты деревомъ. Потолокъ или крыша состоятъ изъ центральной балки и двухъ склоновъ, идущихъ отъ балки къ стѣнамъ. Въ верхней части одного изъ склоновъ имѣется квадратное отверстіе—окно съ рамой, обтянутой перепонкой изъ тюленьихъ внутренностей или пузыря. Это окно имѣетъ еще верхнюю крышку, которой оно закрывается на ночь. Широкая нара, нѣсколько наклонная въ сторону стѣны (см. фиг. 26, *b*), находится на высотѣ отъ пола въ 2—3 фута. По двумъ сторонамъ юртъ стоятъ каменные жирники для освѣщенія жилья и сушки надъ ними одежды. По сторо-

намъ тунеля находятся кухня и ямы, служащія кладовыми (см. фиг. 26 *a*). Кухня представляетъ собой небольшую землянку съ отверстіемъ въ потолкѣ.

Фиг. 27.

Фиг. 27 представляетъ наружный видъ землянки, изображенной въ фиг. 26. Она похожа на два соединенныхъ между собой холма. На вершинѣ большого холма видно окно въ жилое помѣщеніе, а на меньшемъ холмѣ отверстіе для спуска въ тунель. Нѣсколько въ сторонѣ отъ землянки устроенъ мостъ на столбахъ, на который эскимосы ставятъ нарты, кладутъ собачью сбрую, сѣти и др. вещи, чтобы собаки не объѣдали ремней на этихъ предметахъ.

Фиг. 28 (по Murdoch'у) изображаетъ внутренность эскимосской землянки изъ области рѣки Мекензи. Особенность этой землянки заключается въ томъ, что она



Фиг. 28.

имѣетъ форму креста, образуемаго тремя нарами и люкомъ съ падающей дверью, черезъ который спускаются въ подземный ходъ. Здѣсь на рисункѣ мы имѣемъ три конца креста: третья нара не показана.

Фиг. 29 показываетъ модель руины подземнаго жилища сѣверо-восточнаго берега Гренландіи, сложеннаго изъ камней. Это зимнее жилище. Шведская экспедиція 1899 г., подъ начальствомъ проф. Натгорста, нашла на сѣверо-востокѣ Гренландіи подъ 70—75° с. ш. слѣды многихъ зимнихъ подземныхъ жилищъ и лѣтнихъ кожаныхъ палатокъ жившихъ нѣкогда тамъ эскимосовъ [1]). По всей вѣроятности, эти эскимосы переселились на югъ или западъ Гренландіи. *a* показываетъ руину (жилое помѣщеніе и подземный ходъ) въ вертикальномъ разрѣзѣ, а *b* внутренность жилого помѣщенія безъ крыши.



Фиг. 29.

Сѣверо-Американскіе индѣйцы. Остатки древнихъ подземныхъ жилищъ или преданія о нихъ были найдены у индѣйцевъ сѣверо-западной Америки, принадлежащихъ, главныхъ образомъ, группамъ салишанъ и атапасковъ. У нѣкоторыхъ племенъ изъ этихъ группъ землянки сохранились и въ настоящее время. Весьма интересно, что береговыя племена сѣверо-западной Америки, какъ тлинкиты, чимшіанъ, гайда, белла-кула и квакіутль, миѳы которыхъ имѣютъ наибольшее сходство съ миѳологіею обитателей подземныхъ жилищъ сибирскихъ береговъ Берингова моря, живутъ въ настоящее время въ обширныхъ над-

[1]) См. *H. Stolpe.* Über die Forschungsergebnisse der schwedischen Grönland-Expedition vom Jahre 1899 (Internationaler Amerikanisten-Kongress, Vierzehnte Tagung, Stuttgart 1904, Erste Hälfte, S. 101).

земныхъ деревянныхъ постройкахъ [1]). Слѣдуетъ, однако, замѣтить, что дома указанныхъ племенъ имѣютъ очагъ безъ трубы, и отверстіе для дыма находится въ крышѣ, подобно дымовому отверстію коряцкихъ, гиляцкихъ и камчадальскихъ жилищъ [2]). У квакіутль, во время топки на очагѣ, раздвигаютъ доски на крышѣ для пропуска дыма. Преданіе племени белла-кулла въ Британской Колумбіи, принадлежащаго къ группѣ салишановъ, указываетъ на то, что они прежде жили въ подземныхъ жилищахъ [3]). Мы находимъ упоминаніе о подземномъ жилищѣ, изъ котораго выходили черезъ дымовое отверстіе въ миѳахъ племени Quinault [4]), тоже принадлежащаго къ группѣ салишанъ, и живущаго теперь на берегу моря въ штатѣ Вашингтонѣ.

У приморскаго племени тсетсаутъ, принадлежащаго къ группѣ атапасковъ, жилище, сдѣланное изъ древесной коры, представляетъ собою, правда, надземную постройку, но для зимы она получаетъ видъ коряцкой землянки. Когда снѣгъ выпадаетъ, дверь закладывается, и входомъ въ жилище начинаетъ служить дымовое отверстіе въ крышѣ [5]).

Подземныя или полу-подземныя жилища существовали прежде и въ нѣкоторыхъ другихъ мѣстахъ Британской Колумбіи, и теперь мы ихъ находимъ у племенъ группы салишанъ, живущихъ внутри страны. Всѣ эти землянки были обитаемы или нынѣ обитаемы исключительно зимою, какъ у камчадаловъ [6]). Дымовое отверстіе въ серединѣ крыши употребляется вмѣсто двери, черезъ которую спускаются въ жилище при помощи зарубленнаго бревна. Какъ у коряковъ и камчадаловъ, очагъ въ этихъ жилищахъ помѣщается у основанія лѣстницы подъ дымовымъ

---

[1]) См. Fifth Report on the North-Western Tribes of Canada (British Association for the Advancement of Science), p. 818.

[2]) *Boas*, Tribes of the North Pacific Coast (Annual Archaeological Report 1905, Toronto, p. 236).

[3]) *Boas*, The Bella-Coola Indians (Publications of the Jesup North Pacific Expedition, Vol. I, Part II), p. 79.

[4]) *Farrand*, Traditions of the Quinault Indians (Publ. of the J. N. Pac. Exped. Vol. II, Part III), p. 94.

[5]) Tenth Report on the North-Western Tribes of Canada (Report of the British Association for the Advancement of Science), 1895, 561.

[6]) Sixth Report on the North-Western Tribes of Canada, pp. 633, 635.

отверстіемъ. Остовъ жилища сдѣланъ изъ жердей или бревенъ. Большею частью эти жилища имѣютъ круглую форму, но встрѣчаются и квадратныя [1]). Яма для жилища выкапывается отъ 12 до 15 футовъ въ діаметрѣ и 4 футовъ глубиною. Крыша покрывается травою или дерномъ, и вся надземная часть обносится землею такъ, что на разстояніи подземныя жилища похожи на круглые холмы, изъ середины которыхъ торчатъ верхнія части зарубленныхъ лѣстницъ. Въ настоящее время мы находимъ такія зимнія жилища у атапасковъ по теченію р. Юкона, у племени шусвапъ [2]), у индѣйцевъ на рѣкѣ Томсонъ [3]), у племени лилуетъ [4]) и у индѣйцевъ нижняго теченія рѣки Фрезеръ [5]).

Остатки древнихъ подземныхъ жилищъ были найдены у племени чилкотинъ [6]), у индѣйцевъ салишанъ въ области рѣки Томсонъ [7]), у индѣйцевъ изъ группы атапасковъ на озерѣ Никола [8]) и во многихъ другихъ мѣстахъ внутри Британской Колумбіи.

Фиг. 30 изображаетъ (по Тейту) планъ землянки, круглой формы, индѣйцевъ р. Томсонъ въ Британской Колумбіи. Фиг. 30 *a* представляетъ вертикальный планъ землянки. Тутъ видно бревно съ зарубками, служащее лѣстницей, и у основанія ея стоитъ камень для защиты лѣстницы отъ огня очага. Фиг. 30 *b* представляетъ круглую крышу землянки и показываетъ ея устройство: балки, идущія отъ четырехъ центральныхъ столбовъ къ окружности ямы; поперечные шесты; участки, покрытые жердями, и часть крыши, обложенной уже дерномъ. Въ серединѣ квадратное входное и дымовое отверстіе, служащее также окномъ, съ верхней частью бревна-лѣстницы.

---

[1]) У атапасковъ на р. Юконѣ встрѣчаются подземныя жилища алеутскаго и эскимосскаго типовъ. (См. Whymper, p. 166).

[2]) Sixth Report of the Norte-Western Tribes of Canada etc. p. 635.

[3]) *Teit*, Thosmon Indians of British Columbia (Publications of the Jesup North Pacifie Exp., vol, Part IV) p. 193.

[4]) *Teit*, The Lilooet Indians, p. 212.

[5]) Sixth Report of the N. W. Tribes of Canada etc., p. 633.

[6]) Twelfth Report of the N. W. Tribes of Canada etc. p. 646.

[7]) *Smith*, The Archaeology of Lytton, British Columbia (Jesnp North Pacifie Expedition, vol. I, Part III; *Idem* Archaeology of Thomson River Indians (J. N. P. Exped. Vol. I, Part VI), p. 403.

[8]) Ibidem, p. 406.

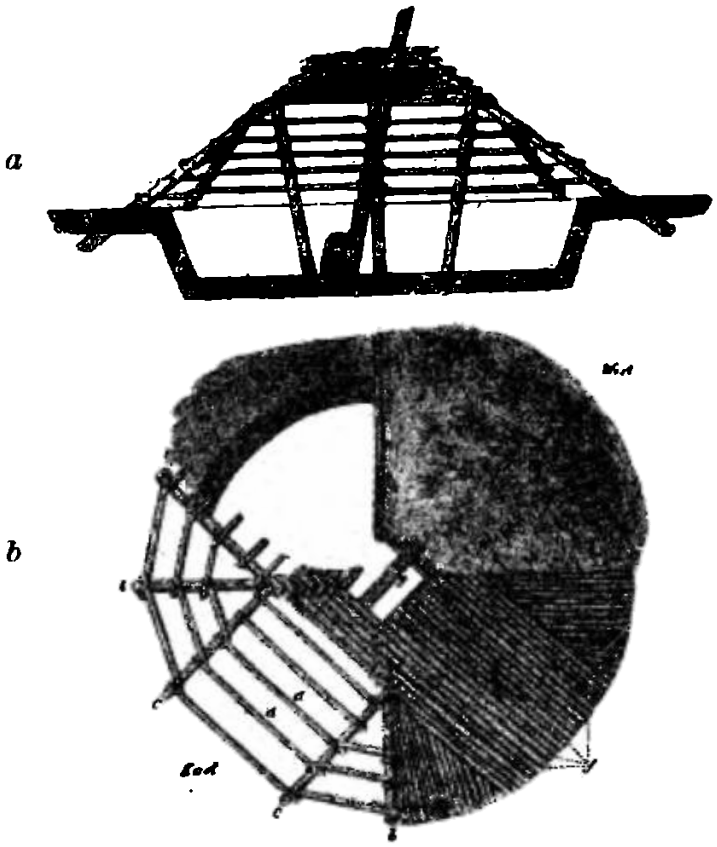

Фиг. 30.

Фиг. 31 [1]) показываетъ наружный видъ землянки,— теперь уже оставленной,—индѣйцевъ рѣки Томсонъ, при-

Фиг. 31.

[1]) Фиг. 31 и 32 воспроизведены изъ «Ethnographical Album of the North Pacific Coasts of America and Asia» Part I, Plates 12, 20 (Jesup North Pacific Expedition, American Museum of Natural History, New-York, 1900).

надлежащихъ къ группѣ салишанъ. а фиг. 32 представляетъ руину другой такой землянки.

Фиг. 32.

Преданія и другіе слѣды прежняго существованія подземныхъ жилищъ мы находимъ также у индѣйцевъ штатовъ Вашингтонъ и Орегонъ [1]). Но особенно интересны остатки землянокъ у различныхъ отдѣловъ племени майду въ штатѣ Калифорніи [2]). Землянки майду имѣли круглую форму, какъ нѣкоторыя землянки племенъ группы салишанъ Британской Колумбіи. Круглая яма, глубиною около метра, обшивалась внутри досками или плахами. Въ серединѣ круга ставили столбы съ перекладинами, отъ которыхъ въ видѣ конуса спускались къ окружности обширной ямы жерди, образующія крышу. Крыша покрывалась землею и дерномъ. Квадратное отверстіе, оставленное въ центрѣ конуса,

---

[1]) *Gatschet*, Klamath Indians of Southwestern Oregon, Contributions N. A. Ethnol. II, 1890. Washington., Part I, pp. 117, 124. *M. Lewis and W Clark*, Original Journals of the Lewis and Clark Expedition, 1804—1806, 7 Vols and Atlas, New York, 1804 - 1805, IV, p. 280, V, p. 35. *G. Gibbs*, Report on the Indian Tribes of the Territory of Washington (Pacific Railroad Report, I, Washington, 1877) p. 409. *H. I. Smith*, Preliminary Notes on the Archaeology of the Yokima Valley, Washington (Science, N. S., XXIII, Apr. 1906) p. 552. *P. Kane*. Wanderings of an Artist among the Indians of North America. London, 1859, p. 272. *A. B. Lewis*. Tribes of the Columbia Valey and the Coast of Washington and Oregon (Memoirs of the American Anthropological Association, Vol. I, Part 2, 1906), p. 185.

[2]) См. *Dixon*, The Northern Maidu (Bulletin of the American Museum of Natural History, vol. XVII, pp. 168 et seq).

служило окномъ, дверью и для выхода дыма. Въ одномъ, сохранившемся и теперь подземномъ домѣ, снимокъ котораго помѣщенъ въ работѣ Диксона о майду, входъ устроенъ сбоку. Но, по словамъ индѣйцевъ, теперешняя боковая дверь когда-то состояла изъ небольшого отверстія, служившаго только для тяги, какъ тунель у камчадаловъ. Подземныя жилища племени майду были большихъ и меньшихъ размѣровъ. Первыя служили клубными помѣщеніями для устройства праздниковъ, общественныхъ собраній, церемоній и также для паровыхъ бань, какъ у эскимосовъ. Землянки меньшаго размѣра служили для жилья. Часто въ домѣ, предназначенномъ для общественныхъ надобностей, жилъ староста селенія. Въ нѣкоторыхъ мѣстахъ въ этихъ подземныхъ жилищахъ жили только зимою, а лѣтомъ ихъ обитатели кочевали, охотясь за дикими животными. Въ другихъ же мѣстахъ въ этихъ жилищахъ жили и лѣтомъ.

Фиг 33.

Фиг. 33 (по Диксону) представляетъ типъ упомянутой выше землянки майду.

Остатки подземныхъ жилищъ встрѣчаются также у племени *Нира* [1]) въ Калифорніи и на плоскогоріи къ

[1]) *Goddard*, Life and Culture of the Hupa (University California Publications, 1903).

востоку отъ Калифорніи. Въ прежнія времена индѣйскія племена Pawnee, Omaha, Arikara, Ponka и Osage въ долинѣ рѣки Миссури жили въ землянкахъ, устроенныхъ въ лѣсу.

Фиг. 34 представляетъ карту областей, племена которыхъ были изслѣдованы экспедиціей Джезупа [1]). Всѣ эти племена жили когда-то или теперь еще живутъ въ подземныхъ юртахъ. Но въ эту карту племенъ, упоминаемыхъ въ этомъ сообщеніи, не вошли восточные эскимосы (эскимосы Гудзонова залива, Гренландіи и Лабрадора) и индѣйцы Вашингтона, Орегона и Калифорніи.

Фиг. 34.

Заключеніе.—Многія изъ подземныхъ жилищъ, упомянутыхъ въ настоящей статьѣ, не были до сихъ поръ достаточно описаны и ждутъ еще болѣе подробнаго изслѣдованія. Тѣмъ не менѣе, этотъ краткій обзоръ является достаточнымъ для того, чтобы вызвать предположеніе, что не всѣ вышеупомянутыя племена явились самостоятельными изобрѣтателями въ устройствѣ подземнаго жилья. Я думаю, что заимствованіе играло тутъ значительную роль, въ то время, какъ климатическія условія содѣйствовали распространенію подземныхъ жилищъ. Матеріалъ, изъ котораго сдѣланы эти подземныя жилища (дерево, кости или камни), не играютъ никакой роли въ опредѣленіи ти-

[1]) См. отчетъ объ экспедиціи въ «The Jesup North Pacific Expedition» (The American Museum Jonrnal. Vol. III, Number 5, Oktober, New-York, 1903).

повъ построекъ, ибо китовыя кости или камни употребляются обыкновенно тамъ, гдѣ лѣсъ трудно достать, или его вовсе нѣтъ, но характерными признаками того или другого типа можно считать слѣдующія части постройки.

1. Тунель, или другое приспособленіе для тяги мы встрѣчаемъ у камчадаловъ, коряковъ, айновъ, курильцевъ, алеутовъ и калифорнскихъ индѣйцевъ.

2. Два входа, одинъ для зимы и другой для лѣта, мы находимъ у коряковъ, чукчей, эскимосовъ сѣверо-западной Америки и у индѣйцевъ тсетсаутъ изъ группы атапасковъ [1]), т. е. у племенъ, живущихъ въ землянкѣ круглый годъ.

3. Квадратное отверстіе въ крышѣ служитъ одновременно дымовымъ, входнымъ и свѣтовымъ—у индѣйцевъ Британской Колумбіи, камчадаловъ, и коряковъ зимой, а въ древности у гиляковъ и индѣйцевъ Калифорніи.

4. Отверстіе въ крышѣ служитъ окномъ и для выхода дыма, но не служитъ дверью, у современныхъ гиляковъ, айновъ, у коряковъ лѣтомъ, у Аляскинскихъ эскимосовъ и современныхъ Калифорнскихъ индѣйцевъ.

5. Отверстіе въ крышѣ служитъ *только* окномъ у чукчей и сѣверо-восточныхъ эскимосовъ, т. е. у тѣхъ племенъ, у которыхъ, за отсутствіемъ дровъ, жилище нагрѣвается жировой лампой.

6. Землянка имѣетъ круглую форму у нѣкорыхъ индѣйцевъ Британской Колумбіи и у Maidu въ Калифорніи.

7. Воронко-образный щитъ отъ вѣтровъ и снѣжныхъ заносовъ имѣется только у коряковъ.

Изъ намѣченныхъ мной главныхъ признаковъ жилищъ разсматриваемаго культурнаго круга, мы видимъ, что сходныя черты встрѣчаются часто въ жилищахъ племенъ, весьма удаленныхъ другъ отъ друга. Это даетъ намъ право предположить, что въ далекомъ прошломъ эти племена имѣли сношенія между собой. Никто, конечно, не станетъ отрицать, что одинаковый типъ подземнаго жилья нашихъ приморскихъ чукчей и эскимосовъ сѣверо-западной Аляски надо приписать культурному вліянію другъ на друга этихъ племенъ, физически различныхъ между собой, вліянію, ко-

---

[1]) См. выше стр. 49.

торое и теперь продолжается. Въ данномъ случаѣ надо думать, что чукчи заимствовали эскимосскій типъ жилья, а не наоборотъ, ибо у родственныхъ чукчамъ племенъ въ Сибири мы *не* встрѣчаемъ этого типа землянки.

Послѣднія изслѣдованія чукчей показали, насколько ихъ миѳы, религія, матеріальный бытъ и семейныя отношенія подверглись вліянію эскимосовъ [1]).

Съ другой стороны изслѣдованія болѣе южныхъ племенъ, какъ коряковъ и камчадаловъ, доказали сходство ихъ миѳовъ, техники, декоративнаго искусства и другихъ сторонъ быта съ миѳами и т. д. сѣверо-западныхъ индѣйцевъ [2]).

Изъ сходства духовной и матеріальной культуры этихъ племенъ мы вправѣ дѣлать заключеніе, что въ древнія времена они имѣли между собою сношенія. Такъ и подземныя жилища племенъ тихоокеанскаго круга надо разсматривать, какъ продуктъ культуры, созданной не изолированнымъ творчествомъ отдѣльныхъ племенъ, а совокупными усиліями многихъ народностей, сообщавшихся между собой и вліявшихъ другъ на друга.

Вл. Іохельсонъ.

---

[1]) См. *Bogoras*, The Folk-Lore of Northeastern Asia as compared with that of Northwestern America (Amer. Anthropologist, vol. IV, October-December, 1902); *idem*, The Chukchee, Part I, Material Culture, Part II, Religion (Publications of the Jesup North-Pacific Expedition, vol. VII, Parts I—II). Leiden, 1904—1907.

[2]) См. *Jochelson*. The Mythology of the Koryak (Amer. Anthropol. Vol. VI, № 4, 1904); *idem* Über asiatische und amerikanische Elemente in den Mythen der Koriaken (Americanisten Kongress, Stuttgart); *idem*, The Koryak, Part I, Religion and Myths. Leiden, 1905, Part II, Material Culture and Social Organisation, Leiden, 1908 (Public. of the J. N. Pac. Exp. Vol. VI, Parts I—II).